CORREDOR PASO LAS LEÑAS

Propuesta territorial del acceso argentino · El Sosneado – portal N4 · Prefactibilidad

Lámina 1/4. Área: corredor El Sosneado – portal N4, Mendoza. Propósito: mostrar dónde pasa la propuesta, qué obras e instalaciones incluye y qué mejora frente a lo existente. Lo existente va con los colores de la carta IGN; lo propuesto, en morado.

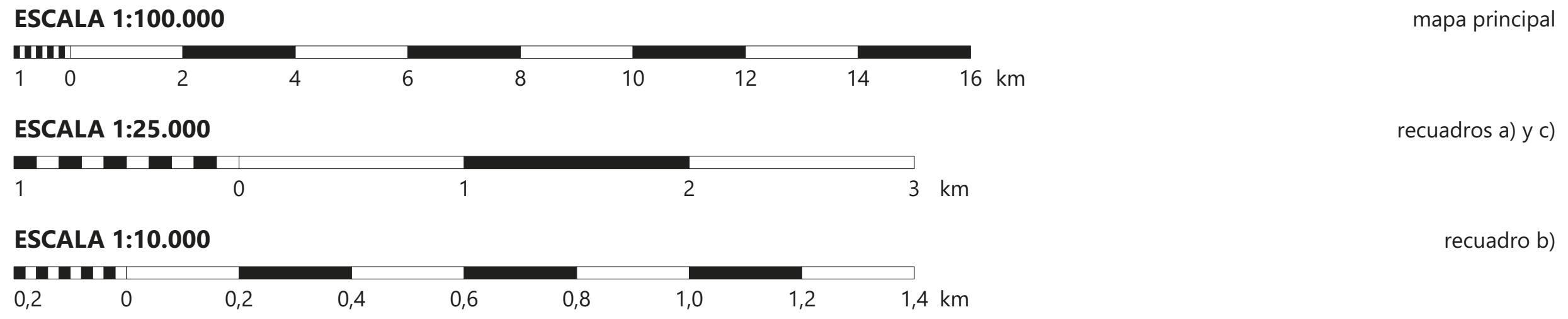
ESCALA 1:100.000
1 0 2 4 6 8 10 12 14 16 km
mapa principal
ESCALA 1:25.000
1 0 1 2 3 km
recuadros a) y c)
ESCALA 1:10.000
0,2 0 0,2 0,4 0,6 0,8 1,0 1,2 1,4 km
recuadro b)

Mapa principal: corredor El Sosneado – portal N4 y túnel hasta el portal chileno

Escala 1:100.000 · curvas cada 50 m (directriz 250 m)

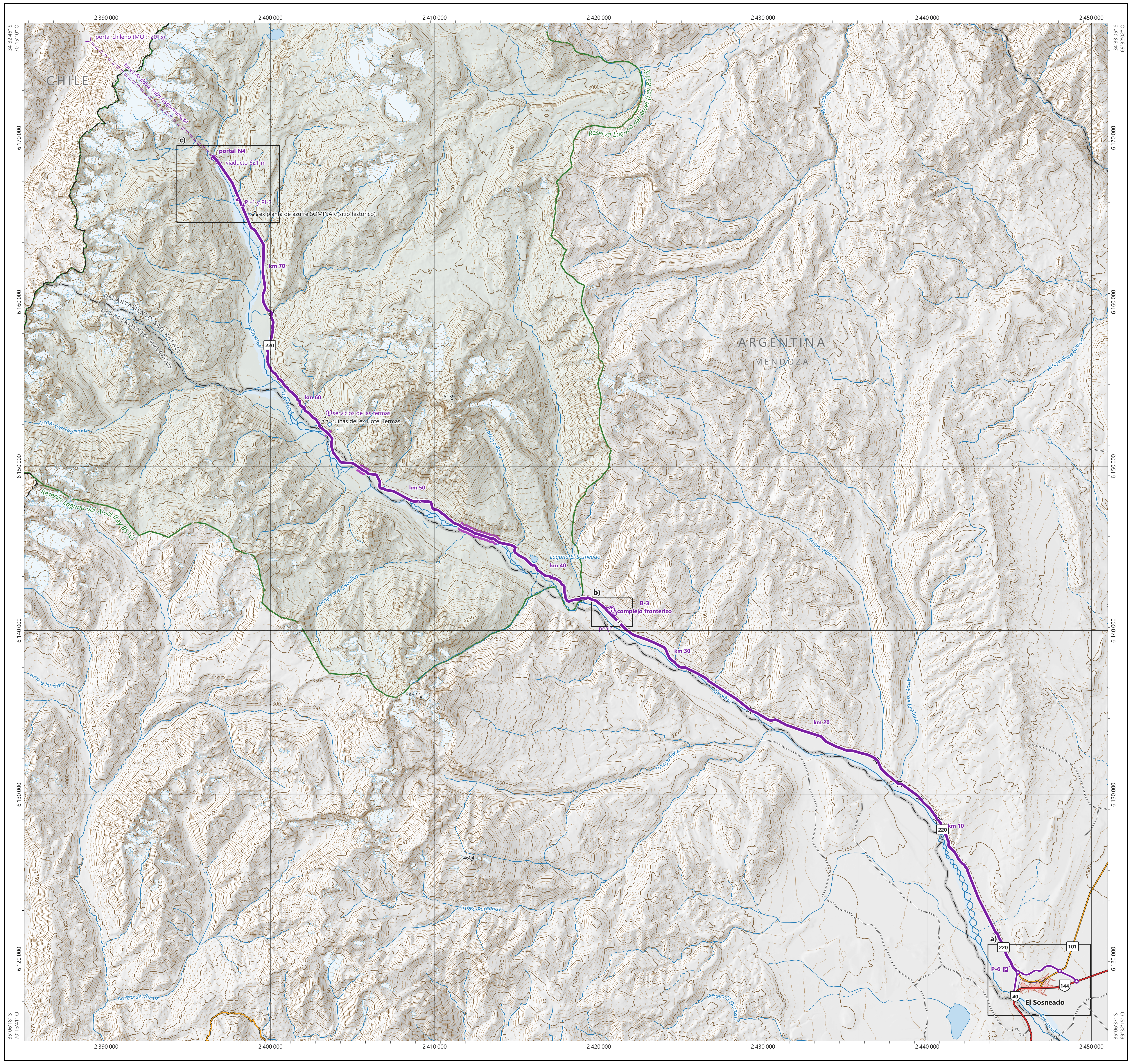
2 390 000
2 400 000
2 410 000
2 420 000
2 430 000
2 440 000
2 450 000
6 170 000
6 160 000
6 150 000
6 140 000
6 130 000
6 120 000
34°32'46" S 70°15'10" O
34°33'05" S 69°32'02" O
35°06'18" S 70°15'41" O
35°06'37" S 69°32'15" O
portal chileno (MOP, 2015)
túnel de doble tubo (esquemático)
CHILE
c)
portal N4
viaducto 621 m
PI-1 y PI-2
ex planta de azufre SOMINAR (sitio histórico)
km 70
Reserva Laguna del Atuel (Ley 8516)
DEPARTAMENTO SAN RAFAEL
DEPARTAMENTO MALARGÜE
Río Atuel
220
km 60
5139
servicios de las termas
ruinas del ex Hotel Termas
F.T.
Arroyo Las Lágrimas
Arroyo Bayo
km 50
Laguna El Sosneado
km 40
b)
B-3
complejo fronterizo
peaje
Arroyo Los Caballos
ARGENTINA
MENDOZA
Río Blanco
Arroyo Seco Blanco
Arroyo Blanco
Arroyo de la Manga
km 30
km 20
km 10
Arroyo La Línea
4922
4604
Arroyo Felipe
Arroyo Paraguay
Arroyo del Burro
Arroyo El Durazno
a)
101
P-6
144
40
El Sosneado

a) El Sosneado: rutas que llegan, desvío, rotondas, parador P-6 y zona de amortiguación

Escala 1:25.000 · curvas cada 10 m (directriz 50 m)

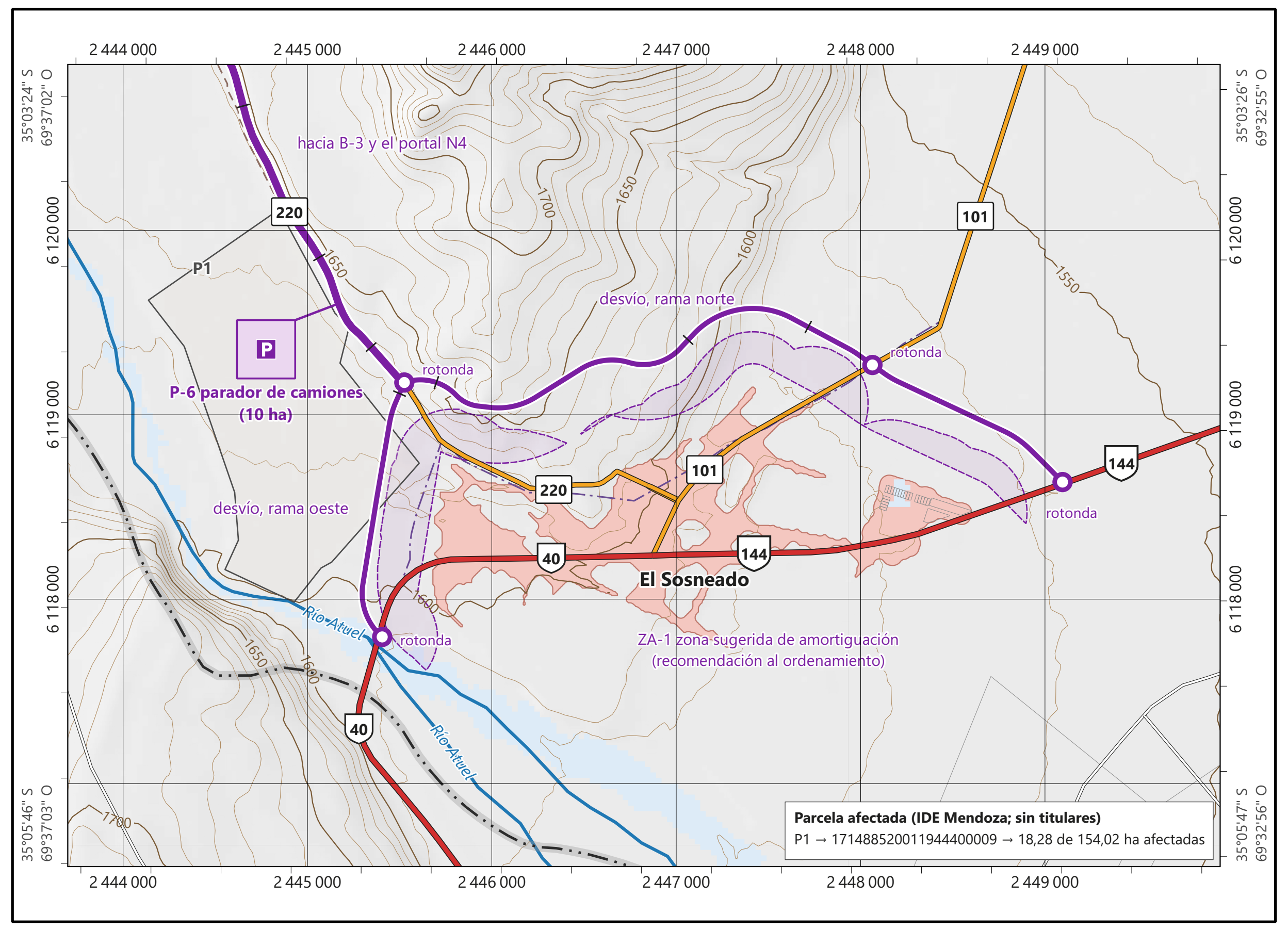
2 444 000
2 445 000
2 446 000
2 447 000
2 448 000
2 449 000
6 120 000
6 119 000
6 118 000
35°03'24" S 69°37'02" O
35°03'26" S 69°32'55" O
35°05'46" S 69°37'03" O
35°05'47" S 69°32'56" O
hacia B-3 y el portal N4
220
P1
P
P-6 parador de camiones (10 ha)
rotonda
desvío, rama norte
101
rotonda
220
101
144
rotonda
desvío, rama oeste
40
144
El Sosneado
rotonda
ZA-1 zona sugerida de amortiguación (recomendación al ordenamiento)
Río Atuel
40

Parcela afectada (IDE Mendoza; sin titulares)

P1 → 17148852001194400009 → 18,28 de 154,02 ha afectadas

b) Complejo B-3: plaza de peaje, carriles y circulación

Escala 1:10.000 · curvas cada 10 m (directriz 50 m)

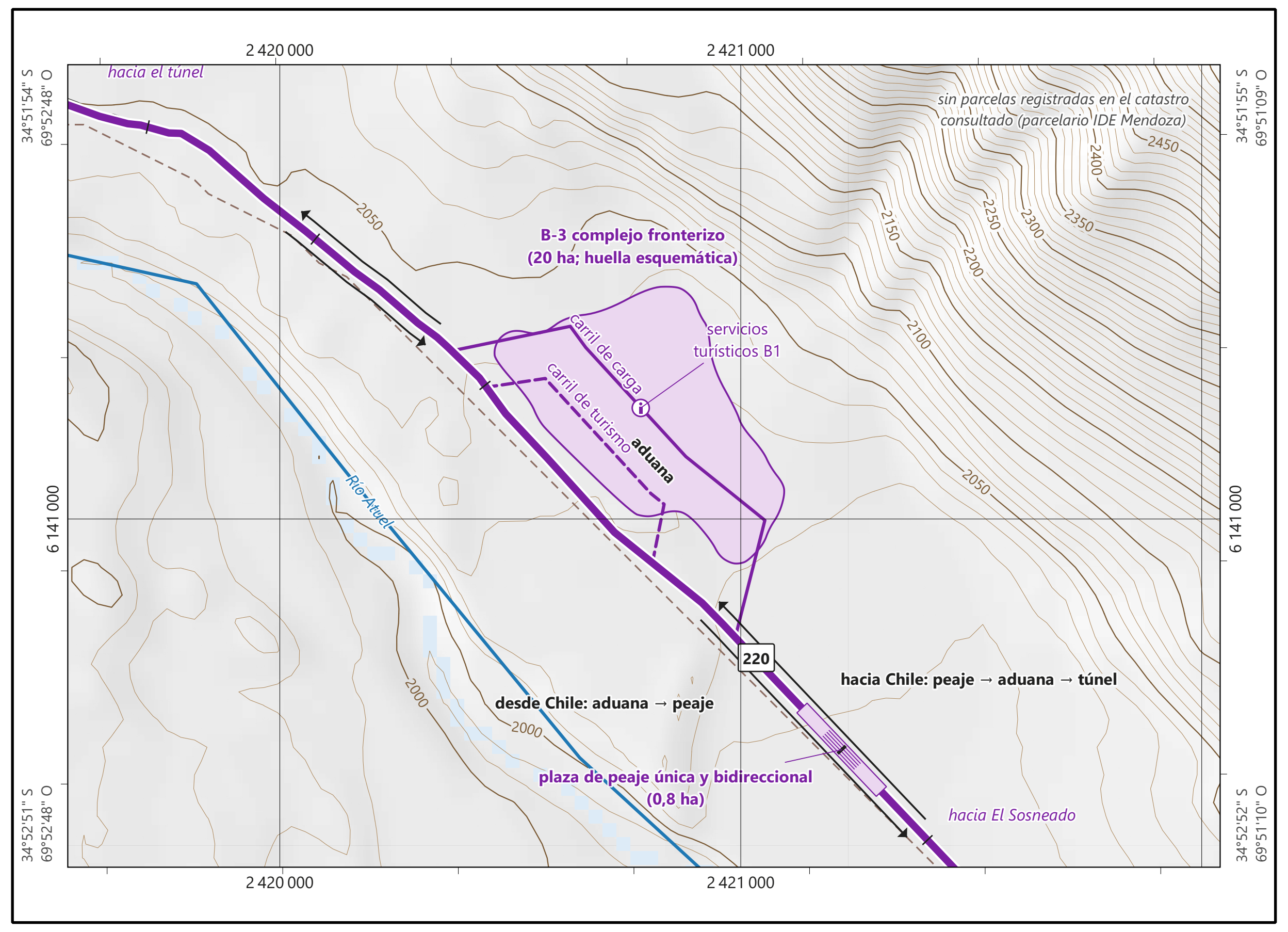
2 420 000
2 421 000
6 141 000
34°51'54" S 69°52'48" O
34°51'55" S 69°51'09" O
34°52'51" S 69°52'48" O
34°52'52" S 69°51'10" O
hacia el túnel
sin parcelas registradas en el catastro consultado (parcelario IDE Mendoza)
B-3 complejo fronterizo (20 ha; huella esquemática)
servicios turísticos B1
carril de carga
carril de turismo
aduana
Río Atuel
220
hacia Chile: peaje → aduana → túnel
desde Chile: aduana → peaje
plaza de peaje única y bidireccional (0,8 ha)
hacia El Sosneado

c) Llegada al portal N4: viaducto, doble calzada, cobertizo, bocas y puestos

Escala 1:25.000 · curvas cada 10 m (directriz 50 m)

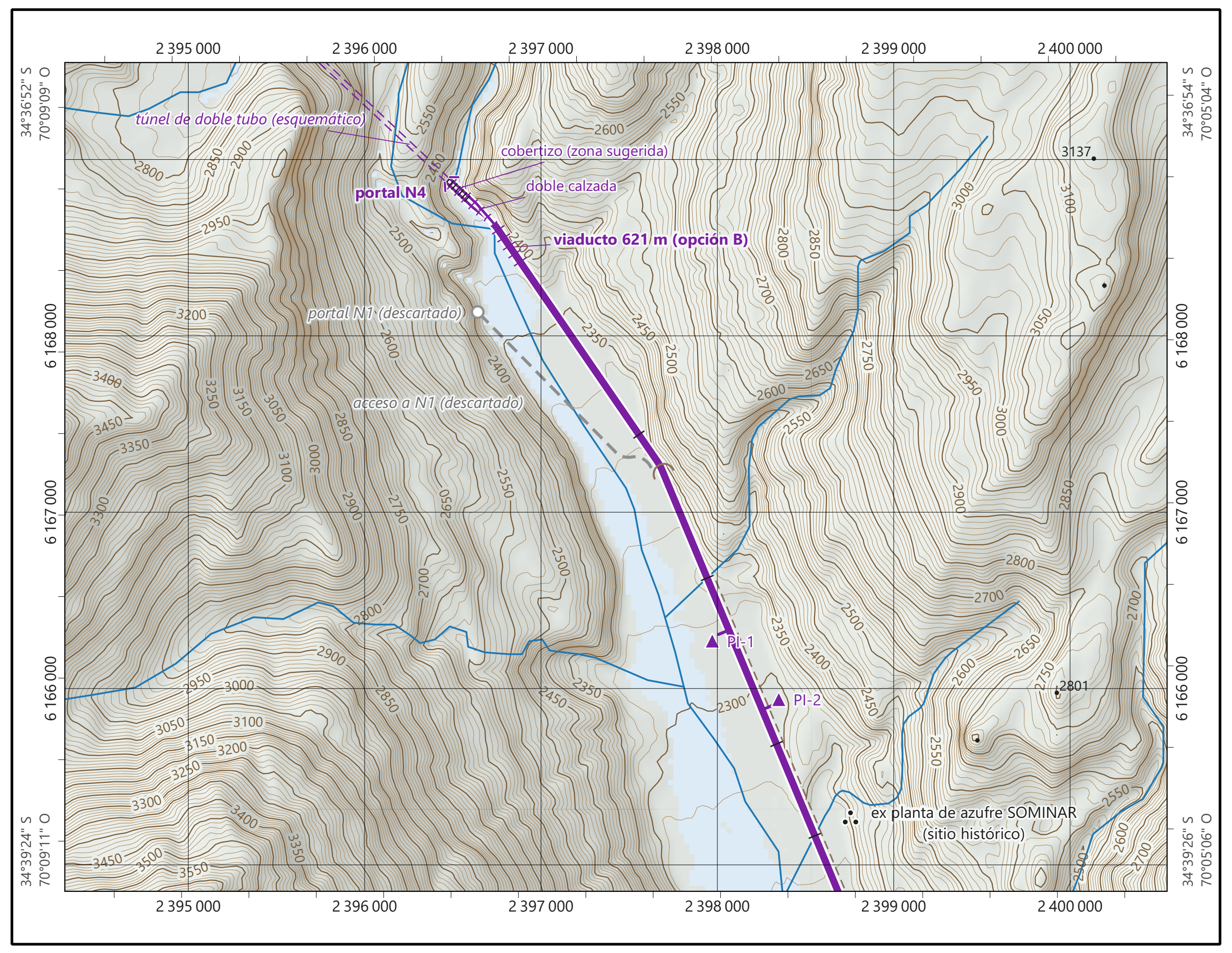
2 395 000
2 396 000
2 397 000
2 398 000
2 399 000
2 400 000
6 168 000
6 167 000
6 166 000
34°36'52" S 70°09'09" O
34°36'54" S 70°05'04" O
34°39'24" S 70°09'11" O
34°39'26" S 70°05'06" O
túnel de doble tubo (esquemático)
cobertizo (zona sugerida)
portal N4
doble calzada
viaducto 621 m (opción B)
portal N1 (descartado)
acceso a N1 (descartado)
3137
PI-1
PI-2
2801
ex planta de azufre SOMINAR (sitio histórico)

UBICACIÓN

Océano Pacífico
ARGENTINA
Océano Atlántico

Argentina y Chile
1:55.000.000

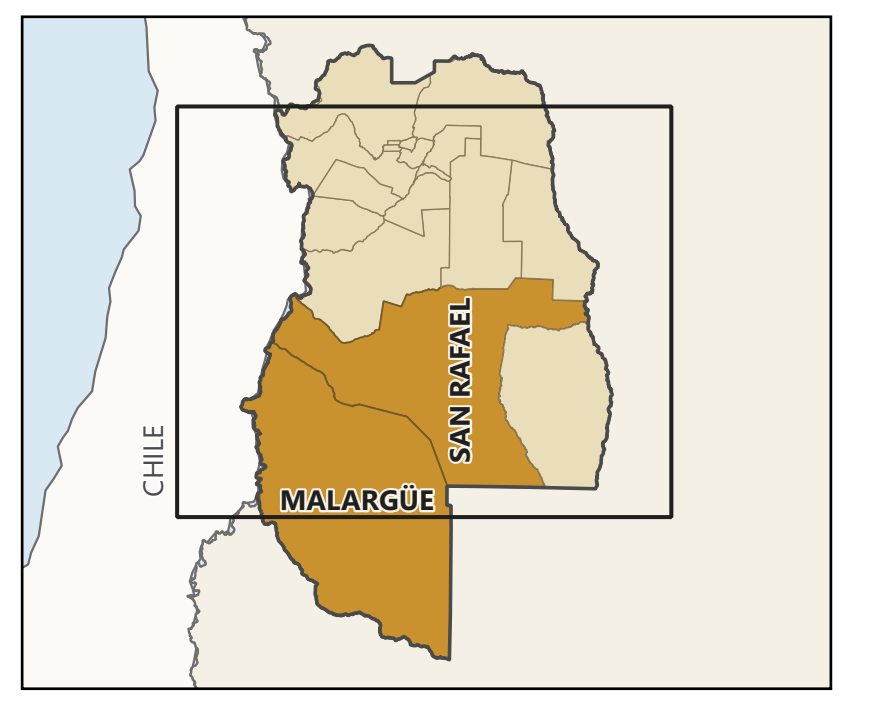
CHILE
SAN RAFAEL
MALARGÜE

Mendoza: departamentos
1:9.000.000

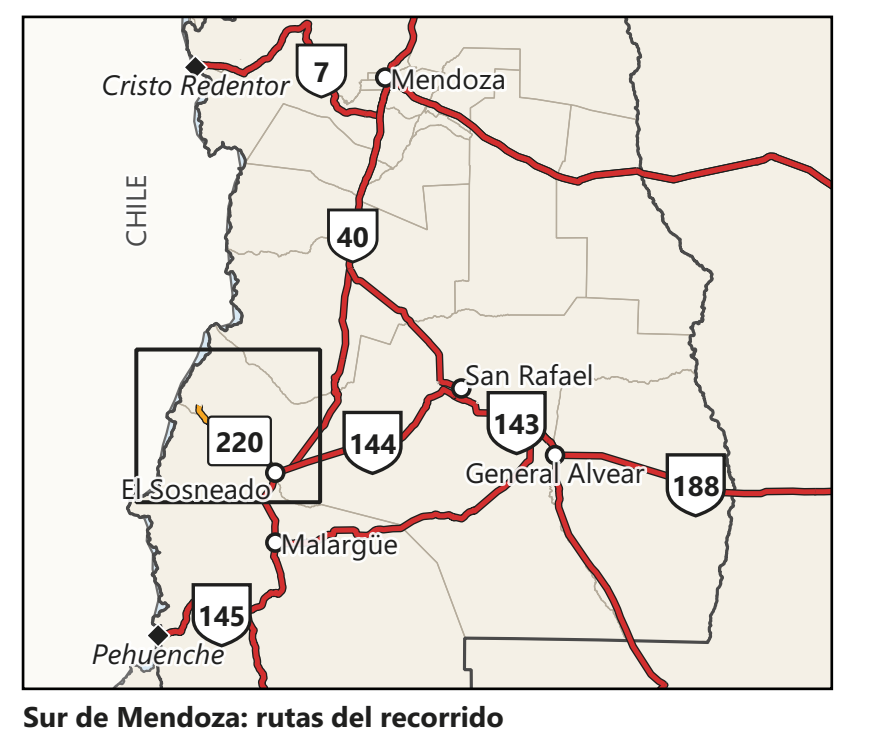
Cristo Redentor
7
Mendoza
CHILE
40
San Rafael
143
220
144
El Sosneado
General Alvear
188
Malargüe
145
Pehuenche

Sur de Mendoza: rutas del recorrido
1:5.500.000

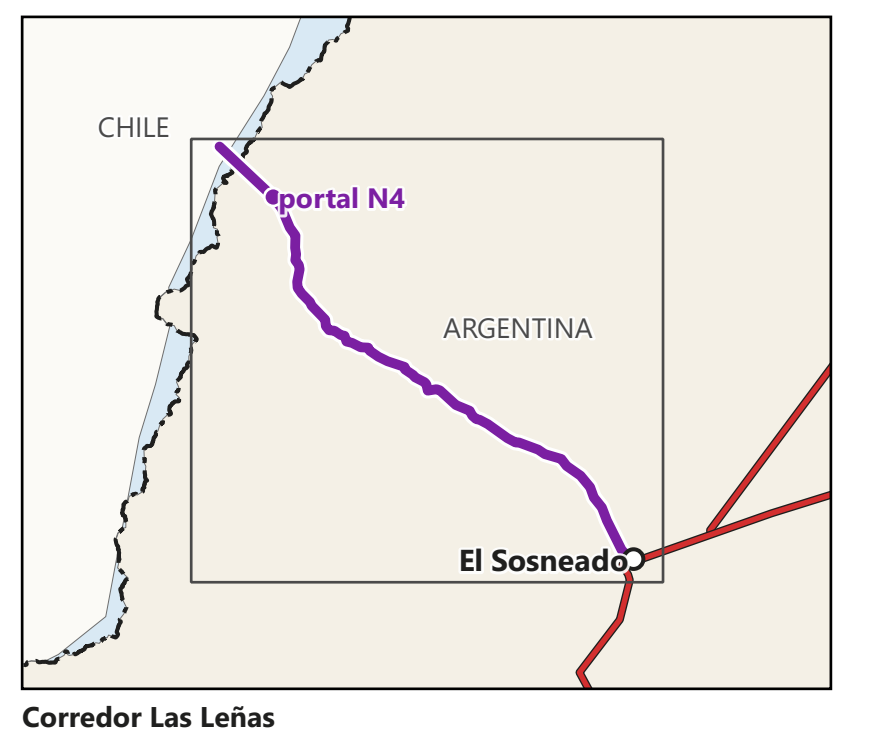
CHILE
portal N4
ARGENTINA
El Sosneado

Corredor Las Leñas
1:1.250.000

Argentina: IGN (con Malvinas); otros países: Natural Earth (04/11/2026). Departamentos: IDE Mendoza (05/11/2026). Rutas: IGN (05/11/2026; RP 220, 02/11/2026). Localidades: BAHRA, IGN (05/11/2026). Rombo: paso internacional. En cada recuadro, el rectángulo es lo que muestra el siguiente.

REFERENCIAS

PROPUESTA (en morado)

- Tronco: El Sosneado – portal N4 (77,5 km)
- Desvío de El Sosneado (rama norte y rama oeste; 5,5 km)
- Accesos (parador P-6 y puestos intermedios)
- Túnel de doble tubo (eje esquemático)
- Boca de túnel (signo 124.2)
- Viaducto de la llegada a N4 (621 m; signo 126.2)
- Doble calzada del acceso al portal
- Zona sugerida de cobertizo para nieve (signo 125)
- Progresiva del tronco (km)
- Zona sugerida de amortiguación ZA-1 (recomendación al ordenamiento, sin cartografía normativa)

INSTALACIONES (signos propios)

- Complejo fronterizo B-3 (20 ha, referencia ACI Uspallata; huella esquemática)
- Plaza de peaje única y bidireccional, fuera del complejo (0,8 ha); a 1:10.000, plataforma con islas y línea de cabinas (esquemáticas)
- Carril de carga del complejo (esquemático)
- Carril de turismo del complejo (esquemático)
- P Parador de camiones P-6 (10 ha)
- ⓘ Servicios turísticos: B1 junto a B-3; en las termas, estacionamiento, sanitarios y señalización
- → Circulación en el recuadro b) (esquemática)
- ▲ Puestos intermedios PI-1 y PI-2; apartaderos AP-1 y AP-2

OBRAS

- Puente (signo 127; 9 puentes)
- Tramo junto al río Atuel (defensa de margen; 3 tramos)
- Alcantarilla u obra de cono (signo 136.2; solo a 1:25.000)
- ○ Rotonda (art. 74)
- Senda de arreo sugerida (73,6 km; supuesto de trabajo; signo 47 por su forma); a 1:100.000, desplazada del tronco para que se lea
- Paso de hacienda a nivel, con señalización (21; solo a 1:25.000)
- Paso de hacienda inferior (15; solo a 1:25.000)

RESTRICCIONES NORMATIVAS

- Reserva de Recursos y Reserva Hídrica Natural Laguna del Atuel (Ley 8516; signo 227)
- Límite de la Zona de Seguridad de Frontera (signo 228; solo línea)
- Glaciares y ambiente periglacial (IANIGLA v1.2; Ley 26.639; signo 73.2)

BASE (lo existente)

- Ruta nacional pavimentada: RN 40 y RN 144 (signo 42)
- Ruta provincial consolidada: RP 101 y RP 220 existente (signo 43)
- Numeración vial: nacional (signo 50.1)
- Numeración vial: provincial (signo 50.2)
- Camino de tierra (signo 45)
- Huella (signo 46)
- Corriente de agua perenne (signo 1)
- Corriente de agua intermitente (signo 2)
- Laguna (signo 5)
- Lecho activo o agua visibles (Sentinel-2; signo propio)
- Curva directriz, cada 250 m; en los recuadros, cada 50 m (signo 236.1)
- Curva intermedia, cada 50 m; en los recuadros, cada 10 m (signo 236.2)
- • Cota del terreno en metros, derivada del MDE (signo 249.2)
- Área urbana de El Sosneado
- Límite de parcela (parcelario IDE Mendoza; solo en los recuadros a) y b))
- Parcela con afectación parcelaria: P1 (nomenclatura y superficie en la tabla del recuadro a)
- Límite internacional (signo 223)
- Límite departamental
- ∴ Ruinas (signo 180): ex Hotel Termas; ex planta de azufre SOMINAR (sitio histórico)
- ○ Fuente termal, F.T. (signo 11)

DESCARTADOS (en gris, solo en el recuadro c)

- Acceso a N1 y su viaducto
- ○ Portal N1

DIAGRAMA DE NORTES

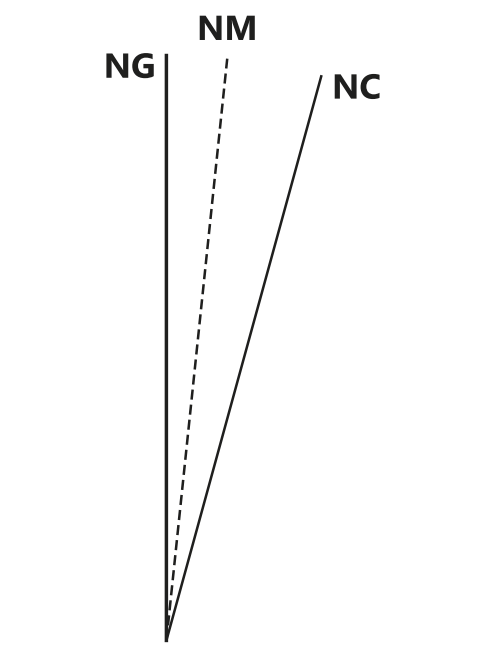

NG: norte geográfico (meridiano). NC: norte de cuadrícula; convergencia 0,51° (NG al oeste de NC). NM: norte magnético; declinación +0,20° E, variación −0,18°/año (WMM2025, 17/11/2026; centro del corredor). Ángulos exagerados ×30.

ENSAMBLE DE HOJAS IGN 1:100.000

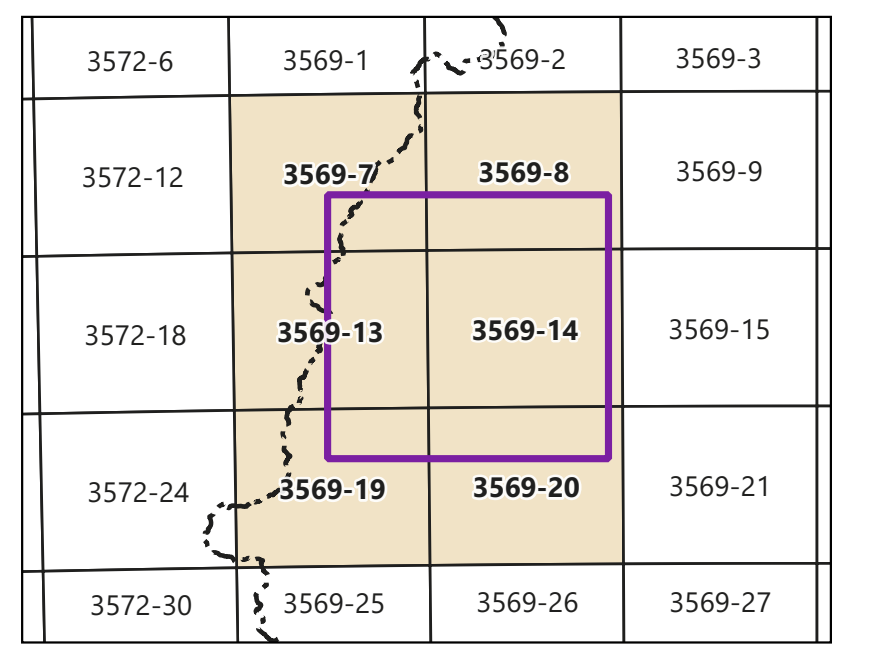

3572-6	3569-1	3569-2	3569-3
3572-12	3569-7	3569-8	3569-9
3572-18	3569-13	3569-14	3569-15
3572-24	3569-19	3569-20	3569-21
3572-30	3569-25	3569-26	3569-27

En color, las hojas que abarca el mapa principal (contorno morado): 3569-7, 3569-8, 3569-13, 3569-14, 3569-19 y 3569-20. Raya y punto: límite internacional (signo 223); al oeste, Chile. Nomenclatura IGN (Manual 2010, p. 19). Escala del panel 1:2.100.000.

EL PROBLEMA

· El Cristo Redentor tiene ~45 días al año con restricción por nevadas (MOP, 2015).

· De San Rafael a Santiago hoy son 538 km por ese paso.

· La RP 220 entra a El Sosneado: 1,86 km de tránsito pesado por el pueblo.

· Tiene 0,39 km sobre la pendiente absoluta (norma DNV) y 324 m en lecho activo.

Alternativas comparadas (N4 frente a N1, desvíos, llegada a N4), criterios de elección y costos: lámina 4/4. Orden de magnitud de prefactibilidad sobre un DSM de 30 m: no es diseño ni presupuesto.

→

LA PROPUESTA

· Desvío de El Sosneado (5,5 km), a 334 m del área urbana como mínimo.

· Tronco de 77,5 km: RP 220 mejorada y 10,6 km de traza nueva.

· Llegada en viaducto (621 m) y túnel de doble tubo, con 7,48 km en Argentina.

· Complejo B-3 fuera de la Reserva, con plaza de peaje a unos 300 m y servicios turísticos; parador P-6.

· Senda de arreo (73,6 km) y 36 pasos de hacienda: supuesto de trabajo, a validar con los puesteros.

Relieve: sombreado multidireccional gris (30 %) del MDE; curvas sepia cada 50 m en el mapa principal y cada 10 m en los recuadros, salvo aclaración (art. 268); cotas en metros. Rótulos GK en metros.

→

LA MEJORA ESPERADA

· Tránsito pesado por el pueblo: de 1,86 a 0 km. Sobre la absoluta: de 0,39 a 0 km.

· Lecho activo: de 324 a 176 m. Senda de arreo separada de la calzada, salvo 1,5 km.

· 17,8 ha de instalaciones que no se construyen en la Reserva.

· San Rafael – Santiago: 404 km en lugar de 538 (−25 %).

· Contrapartidas: 97.100 m³ de movimiento de suelos y un cruce de cauce más (156 a 157).

A 1:100.000 solo se dibujan los 9 puentes, el viaducto y la franja de los 3 tramos junto al río Atuel: las 126 obras agrupadas, con las alcantarillas, están en la lámina 3/4. Los signos que a 1:100.000 caen bajo el tronco (ruinas, servicios de las termas, F.T., SOMINAR) se corren hacia el lado del eje donde está cada objeto.

UNIVERSIDAD
MAZA

LÁMINA 1/4

CARTA PRINCIPAL: CORREDOR PASO LAS LEÑAS

INGENIERÍA EN AGRIMENSURA
FAC. DE INGENIERÍA Y ENOLOGÍA - UMAZA
TRABAJO FINAL - CARTOGRAFÍA APLICADA
PROF. ING. AGRIM. LAUTARO MARTÍNEZ
PROF. ING. AGRIM. ÉRICA ESCUDERO
ELABORADO POR: MOSCHELLA LUCA VALENTÍN
FECHA DE ELABORACIÓN: 10/11/2026

Escala 1:100.000; recuadros a) y c) 1:25.000; recuadro b) 1:10.000. Impresión en A0 (1189 × 841 mm).

SRC: POSGAR 2007 / Argentina faja 2 (EPSG:5344), en metros. Cuadrícula GK faja 2; graduación geográfica en el borde (marcas cada 60" y 15" en los recuadros; coordenadas de las esquinas).

MDE: Copernicus GLO-30 (DSM, celda 30 m; descarga 02/11/2026); alturas sobre EGM2008. Equidistancia 50 m (recuadros 10 m). Rasantes y pendientes en %.

Fuentes: IGN (límites, red vial, hidrografía; 02/11/2026); IDE Mendoza (frontera, departamentos; 02/11/2026; parcelario de los recuadros; 02/11/2026); IANIGLA v1.2 (glaciares; 02/11/2026); OSM (huellas, ex planta SOMINAR; 04/11/2026); Sentinel-2 (lecho activo); MOP Chile 2015 (portales, túnel); Natural Earth (croquis; 04/11/2026); Ley 8516; DNV 2010.

Elaboración propia: las fuentes no avalan este trabajo. Signos: Manual de Signos Cartográficos IGN 2010; colores tipo carta IGN; signos propios declarados en la leyenda.

Trabajo académico: no es cartografía oficial ni está aprobado por el IGN.